MẶT CẮT DỰ TÍNH TRỮ LƯỢNG THEO CÁC TUYẾN TỪ T.1 ĐẾN T.9

MỎ ĐÁ XÂY DỰNG NÚI DÀI, XÃ Ô LÂM VÀ XÃ TRI TÔN, TỈNH AN GIANG

TỶ LỆ 1: 5.000

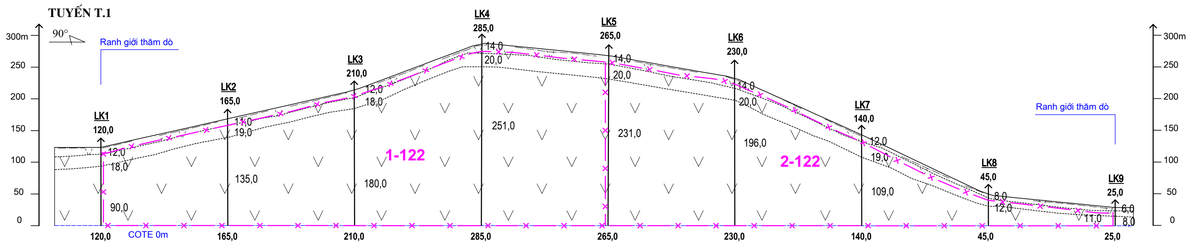

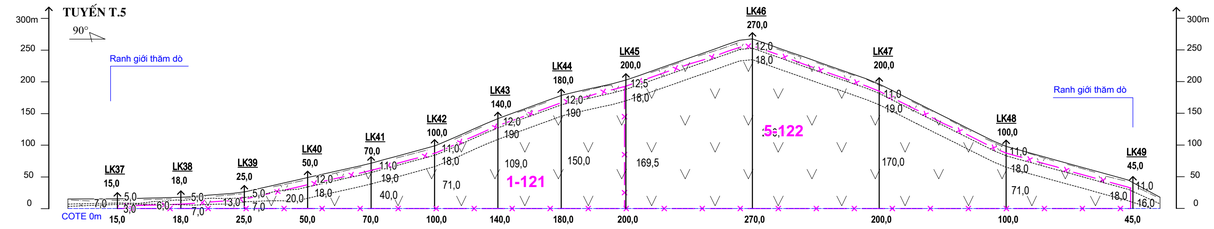

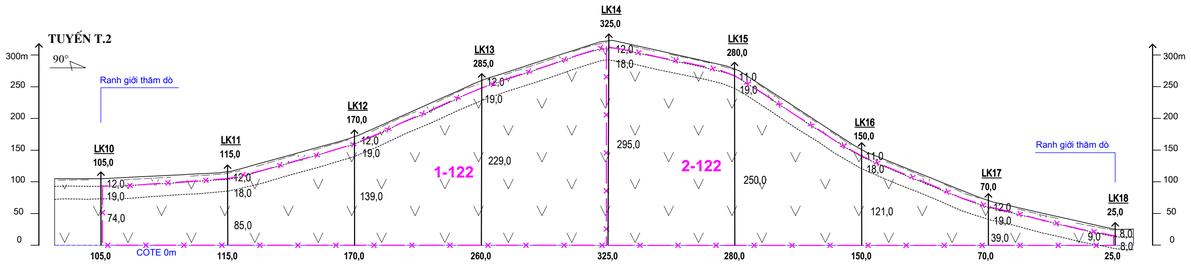

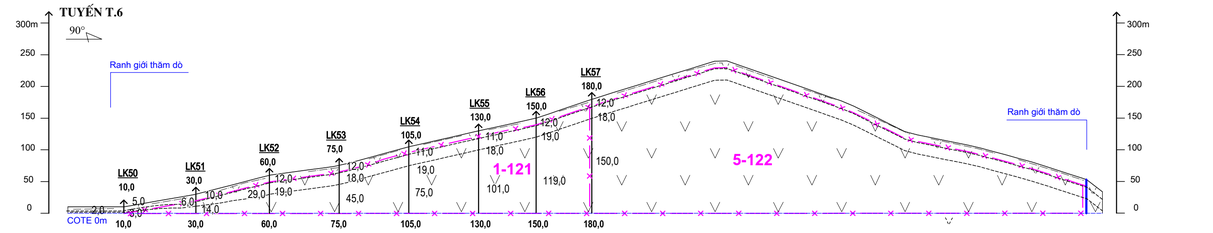

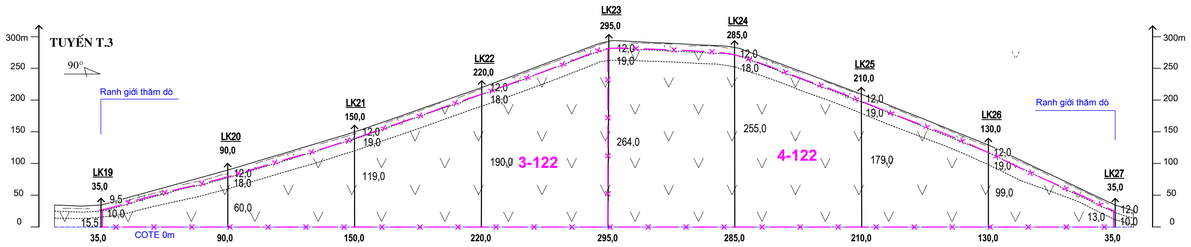

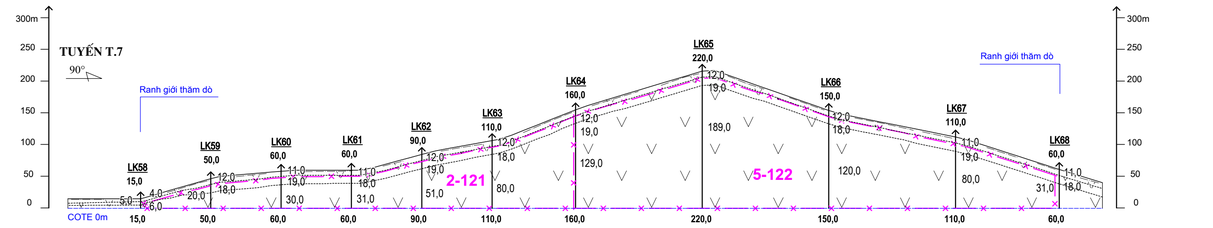

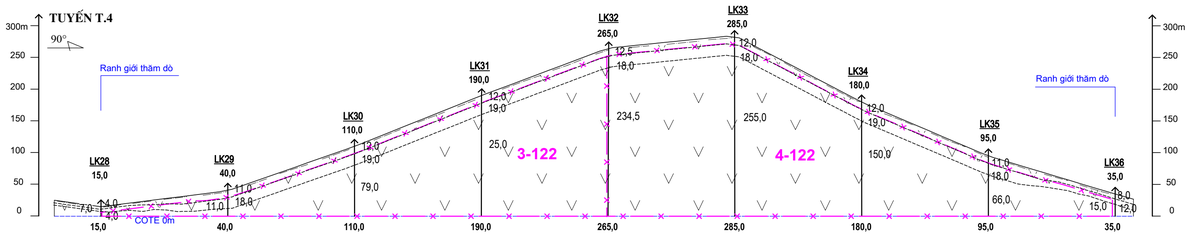

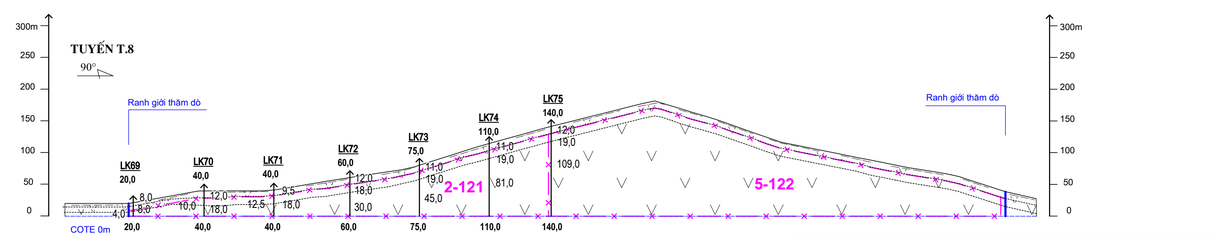

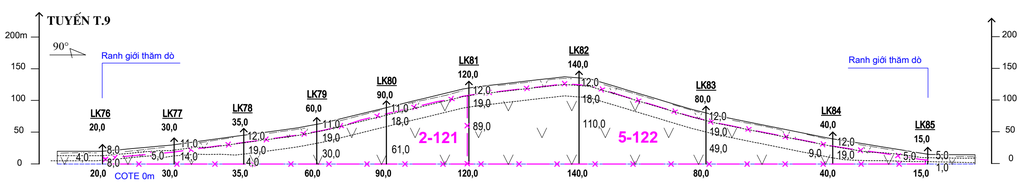

CHỈ DẪN

I. TRỮ LƯỢNG

- Ranh giới phân khối trữ lượng
- 1-121 — Khối, số hiệu và cấp trữ lượng 121
- 3-122 — Khối, số hiệu và cấp trữ lượng 122

II. THẠCH HỌC

Kí hiệu thạch học:

- Cát lẫn sạn sỏi
- Bột sét
- Đá bán phong hóa
- Andesit

Kí hiệu lỗ khoan trên mặt cắt:

1. Số hiệu lỗ khoan;
2. Chiều sâu khoan (m);
3. Cao độ lỗ khoan (m);
4. Bề dày lớp phủ (m);
5. Bề dày lớp bán phong hóa (m);
6. Bề dày lớp đá cứng (m).

- 90° — Phương vị mặt cắt
- Ranh giới thạch học
- Ranh giới địa chất

CÔNG TY TNHH KHOÁNG SẢN THUẬN PHONG		
ĐỀ ÁN THĂM DÒ MỎ ĐÁ XÂY DỰNG NÚI DÀI, XÃ Ô LÂM VÀ XÃ TRI TÔN, TỈNH AN GIANG		
Bản vẽ số: 06	Tỷ lệ 1: 5.000	Năm 2025
MẶT CẮT DỰ TÍNH TRỮ LƯỢNG		
Chức danh	Họ và tên	Kí tên
Người thành lập	Nguyễn Thị Ninh Thanh	
Người kiểm tra	Nguyễn Tiến Dũng	
Chủ nhiệm		
CHỦ ĐẦU TƯ	ĐƠN VỊ TƯ VẤN	