UBND THÀNH PHỐ CẦN THƠ
SỞ NÔNG NGHIỆP VÀ MÔI TRƯỜNG

ĐỀ ÁN THĂM DÒ KHOÁNG SẢN
CÁT SAN LẤP TRÊN SÔNG HẬU TẠI KHU VỰC MỎ PHÚ THỨ – TÂN PHÚ THUỘC PHƯỜNG HƯNG PHÚ, THÀNH PHỐ CẦN THƠ

CHỦ ĐẦU TƯ
CÔNG TY CP KHOÁNG SẢN THUẬN PHONG

ĐƠN VỊ TƯ VẤN
CÔNG TY TNHH MÔI TRƯỜNG VÀ TÀI NGUYÊN MINH ĐỨC

Tp. Cần Thơ, tháng 02 năm 2026

Nội dung báo cáo

1. MỞ ĐẦU
2. KHÁI QUÁT VỀ KHU THĂM DÒ KHOÁNG SẢN
3. ĐẶC ĐIỂM ĐỊA CHẤT KHOÁNG SẢN
4. PHƯƠNG PHÁP VÀ KHỐI LƯỢNG THĂM DÒ
5. DỰ TÍNH TRỮ LƯỢNG KHOÁNG SẢN
6. TỔ CHỨC THI CÔNG
7. DỰ TOÁN KINH PHÍ
8. KẾT LUẬN

1 MỞ ĐẦU

Xuất phát từ nhu cầu sử dụng vật liệu xây dựng thông thường phục vụ phát triển và quy hoạch đầu tư công giai đoạn đến năm 2030, tầm nhìn đến năm 2050, Công ty Cổ phần Khoáng sản Thuận Phong đề xuất được thăm dò khoáng sản cát san lấp trên sông Hậu tại khu vực mỏ Phú Thứ – Tân Phú thuộc phường Hưng Phú, thành phố Cần Thơ, làm cơ sở để tổ chức khai thác hợp lý, đúng quy định pháp luật.

Nguồn cát khai thác từ khu vực mỏ này dự kiến phục vụ trực tiếp cho các công trình đầu tư công trên địa bàn thành phố Cần Thơ, sử dụng vốn ngân sách nhà nước, góp phần bảo đảm nguồn vật liệu ổn định, chủ động, tiết kiệm chi phí và đáp ứng yêu cầu phát triển bền vững của địa phương.

1 MỞ ĐẦU

CĂN CỨ PHÁP LÝ LẬP ĐỀ ÁN

- Luật Địa chất và Khoáng sản số 54/2024/QH15 có hiệu lực kể từ ngày 01/7/2025; Sửa đổi, bổ sung một số điều của Luật địa chất và khoáng sản Luật số 147/2025/QH15 ngày 11/12/2025.

- Nghị định số 193/2025/NĐ-CP ngày 02/7/2025 của Chính phủ quy định chi tiết một số điều và biện pháp thi hành Luật Địa chất và khoáng sản; Nghị định số 21/2026/NĐ-CP ngày 16/01/2026 của Chính phủ sửa đổi, bổ sung một số điều của Nghị định số 193/2025/NĐ-CP ngày 02 tháng 7 năm 2025.

- Nghị quyết số 66.4/2025/NQ-CP ngày 21/9/2025 của Chính phủ về việc ban hành các cơ chế, chính sách đặc thù nhằm tháo gỡ khó khăn trong triển khai Luật Địa chất và khoáng sản năm 2024.

- Thông tư số 40/2025/TT-BNNMT ngày 02/7/2025 của Bộ Nông nghiệp và Môi trường về việc Quy định về phân cấp trữ lượng và tài nguyên khoáng sản; phương pháp, khối lượng công tác thăm dò khoáng sản đối với từng loại khoáng sản; mẫu, nội dung đề án và báo cáo kết quả thăm dò khoáng sản.

- Thông tư số 49/2025/TT-BNNMTngày 19/8/2025 của Bộ Nông nghiệp và Môi trường về việc Quy định kỹ thuật điều tra, đánh giá khoáng sản cát, sỏi lòng sông, lòng hồ.

CĂN CỨ PHÁP LÝ LẬP ĐỀ ÁN

- Quyết định số 1655/QĐ-BTNMT ngày 19 tháng 6 năm 2024 của Bộ TN&MT về việc Ban hành Bộ đơn giá sản phẩm dịch vụ sự nghiệp công lĩnh vực địa chất khoáng sản sử dụng ngân sách nhà nước (theo mức lương cơ sở 1.800.000 đồng/tháng).

- Quyết định số 1519/QĐ-TTg ngày 02/12/2023 của Thủ tướng Chính phủ phê duyệt Quy hoạch thành phố Cần Thơ thời kỳ 2021-2030, tầm nhìn đến năm 2050.

-Quyết định số 3639/QĐ-UBND ngày 31/12/2025 về việc Phê duyệt điều chỉnh Quy hoạch thành phố Cần Thơ thời kỳ 2021 - 2030, tầm nhìn đến năm 2050; phụ lục số XXV.

- Quyết định số 671/QĐ-UBND ngày 11/02/2026 Về việc khoanh định, phê duyệt khu vực không đấu giá quyền khai thác khoáng sản thuộc thẩm quyền cấp giấy phép của Ủy ban nhân dân thành phố Cần Thơ.

- Văn bản số 336 /BQLDA-KHTH ngày 09/02/2026 của Ban QLDA ĐTXD công trình Giao Thông & Nông Nghiệp về việc xem xét cấp phép thăm dò, khai thác mỏ cát san lấp trên địa bàn thành phố Cần Thơ cho Công ty Cổ phần Khoáng sản Thuận Phong

1 MỞ ĐẦU

ĐỐI TƯỢNG KHOÁNG SẢN

- Đối tượng khoáng sản là cát lòng sông và khoáng sản phụ đi kèm (đất bóc tầng phủ) làm vật liệu san lấp.

MỤC TIÊU, NHIỆM VỤ

- Làm sáng tỏ đặc điểm địa chất, địa chất thủy văn, địa chất công trình, điều kiện khai thác mỏ trên diện tích 32,73ha đến độ sâu cote-20m.
- Nghiên cứu, đánh giá chất lượng của các thành tạo địa chất phân bố trong khu vực thăm dò làm vật liệu xây dựng thông thường (cát san lấp, đất bóc tầng phủ để khai thác khoáng sản vật liệu xây dựng thông thường), sản phẩm khai thác chủ yếu dùng để phục vụ các dự án đầu tư công, PPP và các công trình trọng điểm, phát triển kinh tế - xã hội,… trên địa bàn thành phố Cần Thơ.
- Lập báo cáo kết quả thăm dò, đánh giá trữ lượng cát sông và khoáng sản phụ đi kèm có trong mỏ đến cấp 122; trình thẩm định và phê duyệt. Làm cơ sở lập Phương án khai thác để xin giấy phép khai thác mỏ.

THÔNG TIN VỀ TỔ CHỨC ĐỀ NGHỊ CẤP GIẤY PHÉP THĂM DÒ

- Công ty Cổ phần khoáng sản Thuận Phong
- Giấy chứng nhận đăng ký kinh doanh số: 0315214735
- Người đại diện pháp luật: (Ông) Trần Văn Bền

ĐƠN VỊ LẬP ĐỀ ÁN THĂM DÒ

- Công ty TNHH Môi trường và Tài nguyên Minh Đức
- Giấy chứng nhận đăng ký kinh doanh số: 0317125738
- Người đại diện pháp luật (Bà): Trương Khánh Huyền
- Giấy chứng nhận Lâm Thành Lâm - Chủ nhiệm đề án địa chất số do Trường Đại học Tài nguyên và Môi trường Hà Nội cấp

2 KHÁI QUÁT VỀ KHU THĂM DÒ KHOÁNG SẢN

- Khu vực thăm dò cát san lấp trên sông Hậu tại khu vực mỏ Phú Thứ – Tân Phú thuộc phường Hưng Phú, thành phố Cần Thơ (phường Hưng Phú là một phường mới được thành lập từ ngày 01/7/2025, bao gồm toàn bộ địa bàn của ba phường cũ: Hưng Phú, Phú Thứ và Tân Phú thuộc Quận Cái Răng cũ)
- Khu vực thăm dò nằm cách trung tâm thành phố Cần Thơ khoảng 4,0km về phía Đông Nam, cách cầu Cần Thơ (QL1A) 2,4km về phía Đông Nam.

Stt	Điểm góc	Hệ tọa độ VN-2000 Kinh tuyến trục 105^0, múi chiếu 3^0	
		X (m)	Y (m)
1	1	1107355	589833
2	2	1106120	590426
3	3	1106057	590300
4	4	1106300	590110
5	5	1106788	589905
6	6	1107126	589427

- Theo phương án bảo vệ, thăm dò, khai thác và sử dụng khoáng sản thành phố Cần Thơ thời kỳ 2021 - 2030, tầm nhìn đến năm 2050, điểm quy hoạch CSL.QH10_CR có diện tích là 33,8ha

- Tuy nhiên sau khi thực hiện đo đạc thực tế, ghi nhận với tọa độ 06 điểm góc như trên, diện tích đo đạc được là 32,73ha

2 KHÁI QUÁT VỀ KHU THĂM DÒ KHOÁNG SẢN

- Khu vực thăm dò không nằm trong khoanh định các khu vực cấm, tạm thời cấm hoạt động khoáng sản, nằm cách đường bờ sông Hậu như sau:

+ Cách bờ phải khoảng 380m (thuộc phường Hưng Phú), hiện trạng trên bờ là đất thuộc khu công nghiệp Hưng Phú 2A và khu công nghiệp Hưng Phú 2B.

+ Cách bờ trái ít nhất khoảng 595m (thuộc tỉnh Vĩnh Long), hiện trạng trên bờ là đất nông nghiệp, ao nuôi trồng thủy sản

2 KHÁI QUÁT VỀ KHU THĂM DÒ KHOÁNG SẢN

- Địa hình đáy sông khu vực thăm dò dao động từ -0,1m đến -14m, trung bình khoảng -8,0m; cao ở Tây Bắc đoạn gần mốc ranh số 6 và thấp dần về phía Đông Nam.



2 KHÁI QUÁT VỀ KHU THĂM DÒ KHOÁNG SẢN

- Khu vực xin thăm dò đã được quan tâm nghiên cứu từ giai đoạn trước, đáng chú ý có các công trình nghiên cứu sau:
- Năm 2018, Thành phố Cần Thơ đã lập "quy hoạch thăm dò, khai thác, sử dụng khoáng sản thành phố Cần Thơ đến năm 2020, tầm nhìn đến năm 2030"
- Năm 2023, UBND thành phố Cần Thơ đã phê duyệt báo cáo kết quả khảo sát, đánh giá hiện trạng, đề xuất định hướng quản lý, khai thác khoáng sản cát trên lòng sông Tiền, sông Hậu và khoáng sản sét, than bùn trên địa bàn thành phố Cần Thơ
- Năm 2023, Đề án "Điều tra, đánh giá tiềm năng cát, cuội, sỏi lòng sông vùng đồng bằng sông Cửu Long phục vụ phát triển bền vững kinh tế - xã hội" do Liên Đoàn Địa Chất Miền Nam thực hiện.
- Năm 2023, Báo cáo kết quả thăm dò khoáng sản cát lòng sông trên sông Hậu (nhánh trái) thuộc xã Tích Thiện và xã Lục Sĩ Thành, huyện Trà Ôn, tỉnh Vĩnh Long, do Công ty Cổ phần Đầu tư xây dựng và kỹ thuật VNCN E&C làm chủ đầu tư (cùng nằm trên sông Hậu, cách vị trí xin thăm dò khoảng 14km về phía Đông Nam).
- Năm 2025, Báo cáo kết quả thăm dò khoáng sản cát trên sông Hậu thuộc xã Định Yên, huyện Lấp Vò, tỉnh Đồng Tháp, do Công ty TNHH Đông Thành Lấp Vò Đồng Tháp làm chủ đầu tư (cùng nằm trên sông Hậu, cách vị trí xin thăm dò khoảng 42km về phía Tây Bắc).

3 ĐẶC ĐIỂM ĐỊA CHẤT KHOÁNG SẢN

Địa tầng

1. Thống Holocen, phụ thống thượng, trầm tích sông-đầm lầy ($abQ_2^3{}_1$)

Lộ ra trên mặt tạo thành dải rộng kéo dài ở phía Đông Nam bờ sông Hậu, trong khu vực khảo sát

2.Thống Holocen, phụ thống thượng, phần giữa, Trầm tích sông ($aQ_2^3{}_2$)

Phân bố dọc hai bên bờ sông, cù lao sông, đôi chỗ tạo thành dải liên tục

3. Thống Holocen, phụ thống thượng, phần trên, Trầm tích sông hiện đại ($aQ_2^3{}_3$)

Phân bố trong lòng sông tạo thành dải ngầm liên tục. Đây chính là đối tượng thăm dò thành phần trầm tích chủ yếu:

+ Ở khu vực giữa sông vận tốc dòng chảy lớn hơn, thành phần trầm tích thường là cát hạt nhỏ đến trung lẫn vảy mica và mùn thực vật, màu xám nâu đến xám đen.

+ Các đới ven bờ vận tốc dòng chảy yếu, thành phần trầm tích thường là: bùn lẫn mùn thực vật màu xám đen.

3 ĐẶC ĐIỂM ĐỊA CHẤT KHOÁNG SẢN

Địa mạo

1. Địa hình tích tụ

2. Địa hình các cù lao trẻ

3. Đê thiên nhiên ven sông

4. Dạng địa hình tích tụ và xâm thực lòng sông: *Phân bố dưới lòng sông Hậu và thường xuyên bị ngập nước*

Khoáng sản

Khu vực thăm dò và lân cận chỉ có đối tượng khoáng sản là cát sông và khoáng sản phụ đi kèm làm vật liệu san lấp

3 ĐẶC ĐIỂM ĐỊA CHẤT KHOÁNG SẢN

Các tiền đề, dấu hiệu

-Theo báo cáo kết quả khảo sát, đánh giá hiện trạng, đề xuất định hướng quản lý, khai thác khoáng sản cát trên lòng sông Tiền, sông Hậu và khoáng sản sét, than bùn trên địa bàn thành phố Cần Thơ cho thấy vật liệu trong diện tích xin thăm dò có thành phần chủ yếu là cát hạt mịn đến trung, lẫn bùn và mùn thực vật, có khả năng sử dụng để làm vật liệu san lấp

Quy mô khoáng sản

- Toàn bộ diện tích thăm dò chỉ bao gồm 01 thân khoáng cát san lấp là sản phẩm của quá trình bồi tụ, phân bố trên bề mặt địa hình của lòng sông Hậu thuộc trầm tích Holocen thượng, phần trên ($aQ_2^3{}_3$).

-Với diện tích xin thăm dò là 32,73ha, thì đây là một diện tích nhỏ nằm trong thành tạo này. Xét về quy mô thì diện tích thăm dò thuộc loại trung bình

3 ĐẶC ĐIỂM ĐỊA CHẤT KHOÁNG SẢN

Đặc điểm chất lượng khoáng sản

+ Thành phần thạch học và khoáng vật: chủ yếu là thạch anh; ít felspat và mảnh đá sét; mica rất ít; thực vật từ 0 - 1,0%,

+ Thành phần hóa học: hàm lượng SiO2: đạt 80,06 – 82,84%; hàm lượng Al2O3: 7,26 - 8,53%; hàm lượng Na_2O: 1,77 - 2,02%; hàm lượng K_2O: 0,69 - 0,92%. Chất có hại SO_3: 0,00-0,08%.

Đặc điểm phân bố thân khoáng

+ Thân khoáng thường bị phủ lớp bùn, chiều dày từ 1,5 – 3,0m, trung bình 2,2m.

+ Lớp cát màu xám xanh, xám đen lẫn vảy mica hạt mịn, chiều dày từ 1,5 – 3,2m, trung bình 1,5m.

+ Lớp dưới là sét màu xám nâu, nâu đen, chiều dày chưa khống chế.

Thân khoáng nằm ngang, bề dày khá ổn định

4 PHƯƠNG PHÁP VÀ KHỐI LƯỢNG THĂM DÒ

Các văn bản quy phạm pháp luật áp dụng

- Thông tư số 40/2025/TT-BNNMT ngày 02/7/2025 của Bộ Nông nghiệp và Môi trường quy định về phân cấp trữ lượng và tài nguyên khoáng sản; phương pháp, khối lượng thăm dò khoáng sản đối với từng loại khoáng sản; mẫu, nội dung đề án và báo cáo kết quả thăm dò khoáng sản có hiệu lực từ ngày 02/7/2025;

- Thông tư số 49/2025/TT-BNNMT ngày 19/8/2025 của Bộ Nông nghiệp và Môi trường về việc Quy định kỹ thuật điều tra, đánh giá khoáng sản cát, sỏi lòng sông, lòng hồ;

Khu vực dự kiến thăm dò có cấu tạo địa chất đơn giản gồm 1 thân khoáng. Do đó, căn cứ vào quy phạm phân cấp trữ lượng khoáng sản rắn do Bộ Nông nghiệp và Môi trường ban hành có thể xếp khu dự kiến thăm dò vào nhóm mỏ I

Thông tư số 40/2025/TT-BNNMT ngày 02/7/2025 của Bộ Nông nghiệp và Môi trường:

Cấp 122	Tuyến cách nhau tối đa là 400m, công trình trên tuyến tối đa là 200m.

4 PHƯƠNG PHÁP VÀ KHỐI LƯỢNG THĂM DÒ

Từ thực tế diện tích, kích thước khu vực xin thăm dò

+ Đề án bố trí 13 lỗ khoan trên 05 tuyến thăm dò tuyến T.1 đến T.5, khoảng cách giữa 2 tuyến khoảng 310 - 400m; các công trình với khoảng cách từ 120 - 200m.

+ Công trình lỗ khoan dự kiến thi công với độ sâu thăm dò đến cote -20m (cao độ đáy khai thác cát sông cho phép).

Như vậy, với cách bố trí công trình thăm dò trên, toàn bộ trữ lượng trong phạm vi thăm dò đều được xếp vào cấp trữ lượng 122

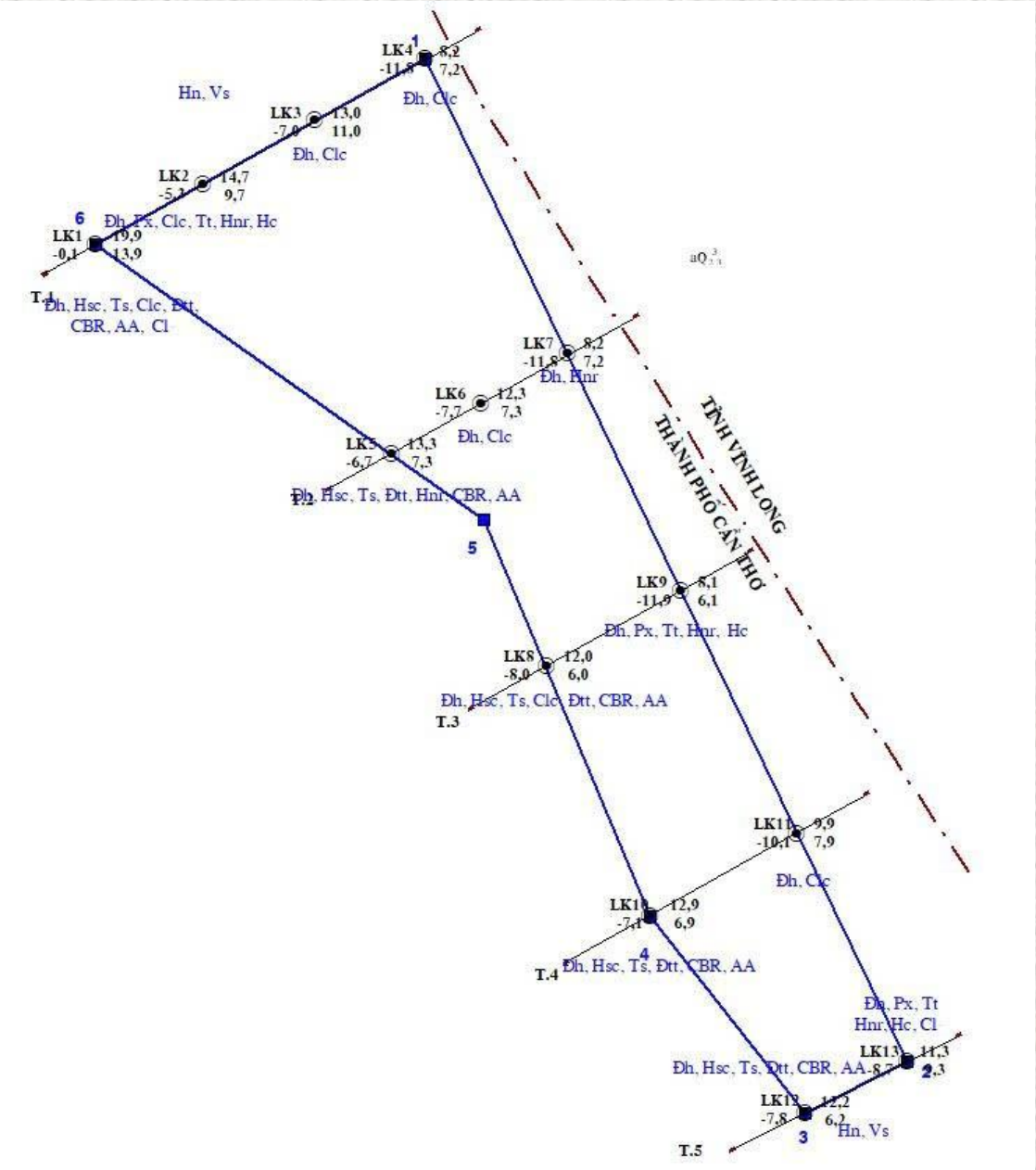

4 PHƯƠNG PHÁP VÀ KHỐI LƯỢNG THĂM DÒ

PHƯƠNG PHÁP VÀ KHỐI LƯỢNG THĂM DÒ

Công tác trắc địa
0,36km²

Công tác lấy, phân tích TN mẫu
75 mẫu với 15 loại mẫu khác nhau

Công tác khảo sát lập bản đồ địa chất
0,36km²

Công tác ĐCTV-ĐCCT
0,36km2

Công tác khoan thăm dò
156m/*13LK*

4 PHƯƠNG PHÁP VÀ KHỐI LƯỢNG THĂM DÒ

Bảng tổng hợp dự kiến khối lượng thi công thăm dò

	Các hạng mục công việc chủ yếu	ĐVT	Khối lượng
1	**Công tác trắc địa**		
1	Trạm quan trắc mực nước sông	tháng/trạm	2
2	Đo GPS nối với 02 điểm địa chính cơ sở hạng III (lưới giải tích 1)	điểm	2
3	Lập lưới khống chế độ cao kỹ thuật	km	4
4	Đo phóng công trình chủ yếu từ bản đồ ra thực địa	công trình	14
5	Đo công trình chủ yếu và đưa vào bản đồ	công trình	13
6	Đo bản đồ địa hình tỷ lệ 1:5.000, h=1m, (phần ngoài trời).	km^2	0,36
7	Đo bản đồ địa hình tỷ lệ 1:5.000, h=1m, (phần trong phòng).	km^2	0,36
2	**Công tác đo vẽ địa chất tỷ lệ 1:5.000**		
	-Ngoại nghiệp	km^2	0,36
	-Nội nghiệp	km^2	0,36
3	**Công tác đo vẽ ĐCTV-ĐCCT tỷ lệ 1:5.000**		
	-Ngoại nghiệp	km^2	0,36
	-Nội nghiệp	km^2	0,36
4	**Công tác khoan thăm dò**		
	Khoan trong đất cát bở rời cấp I-III	m	156
	Tháo lắp vận chuyển thiết bị khoan	lần	13

	Các hạng mục công việc chủ yếu	ĐVT	Khối lượng
5	**Gia công mẫu**		**40**
1	Mẫu độ hạt	mẫu	28
2	Mẫu hóa lý	mẫu	12
6	**Phân tích mẫu**		**75**
1	Mẫu độ hạt cơ bản (Đh)	mẫu	23
2	Mẫu hóa silicat (Hsc)	mẫu	5
3	Mẫu trọng sa (Ts)	mẫu	5
4	Mẫu phóng xạ (Px)	mẫu	3
5	Mẫu cơ lý cát (Clc)	mẫu	5
6	Mẫu độ hạt trầm tích (Đtt)	mẫu	5
6	Mẫu thể trọng (Tt)	mẫu	3
7	Mẫu hệ số nở rời (Hnr)	mẫu	5
8	Mẫu CBR	mẫu	5
9	Mẫu độ hạt AASHTO	mẫu	5
10	Hàm lượng chất hữu cơ	mẫu	3
11	Hàm lượng clorua	mẫu	2
12	Mẫu hóa nước (Hn)	mẫu	2
13	Mẫu vi sinh	mẫu	2
14	Mẫu cơ lý đất (Clđ)	mẫu	2

5 DỰ TÍNH TRỮ LƯỢNG KHOÁNG SẢN

CHỈ TIÊU TÍNH TRỮ LƯỢNG

- Chiều dày thân cát tham gia tính trữ lượng ≥ 1,0m.
- Cote khai thác theo Quy hoạch của UBND thành phố Cần Thơ là -20m.
- Căn cứ theo TCVN 7570:2006 nếu không thoả điều kiện cát xây dựng thì đưa vào cát san lấp.

PHƯƠNG PHÁP TÍNH TRỮ LƯỢNG

$$Q = S \cdot m_{tb}$$

Q: Trữ lượng lớp đất bóc tầng phủ trong khai thác cát và lớp cát lẫn bột sét (m^3)

S: Diện tích khối tính trữ lượng (m^2).

m_{tb}: Bề dày trung bình của đối tượng tham gia tính trữ lượng (m)

Sau này trong báo cáo kết quả thăm dò sẽ sử dụng phương pháp mặt cắt thẳng đứng hoặc phần mềm Sufer để kiểm tra

5 DỰ KIẾN PHƯƠNG PHÁP TÍNH TRỮ LƯỢNG

PHÂN KHỐI VÀ XẾP CẤP TRỮ LƯỢNG

Toàn diện tích thăm dò được chia thành 04 khối: Khối 1-122, 2-122, 3-122 và khối 4-122.

- Khối 1-122 có diện tích 129.470 m^2, được giới hạn bởi các công trình thăm dò LK1, LK2, LK3, LK4, LK5, LK6, LK7.
- Khối 2-122 có diện tích 73.380 m^2, được giới hạn bởi các công trình thăm dò LK5, LK6, LK7, LK8, LK9 và mốc ranh số 5.
- Khối 3-122 có diện tích 70.250m^2, được giới hạn bởi các công trình thăm dò, LK8, LK9, LK10, LK11.
- Khối 4-122 có diện tích 54.200m^2, được giới hạn bởi các công trình thăm dò, LK10, LK11, LK12, LK13.

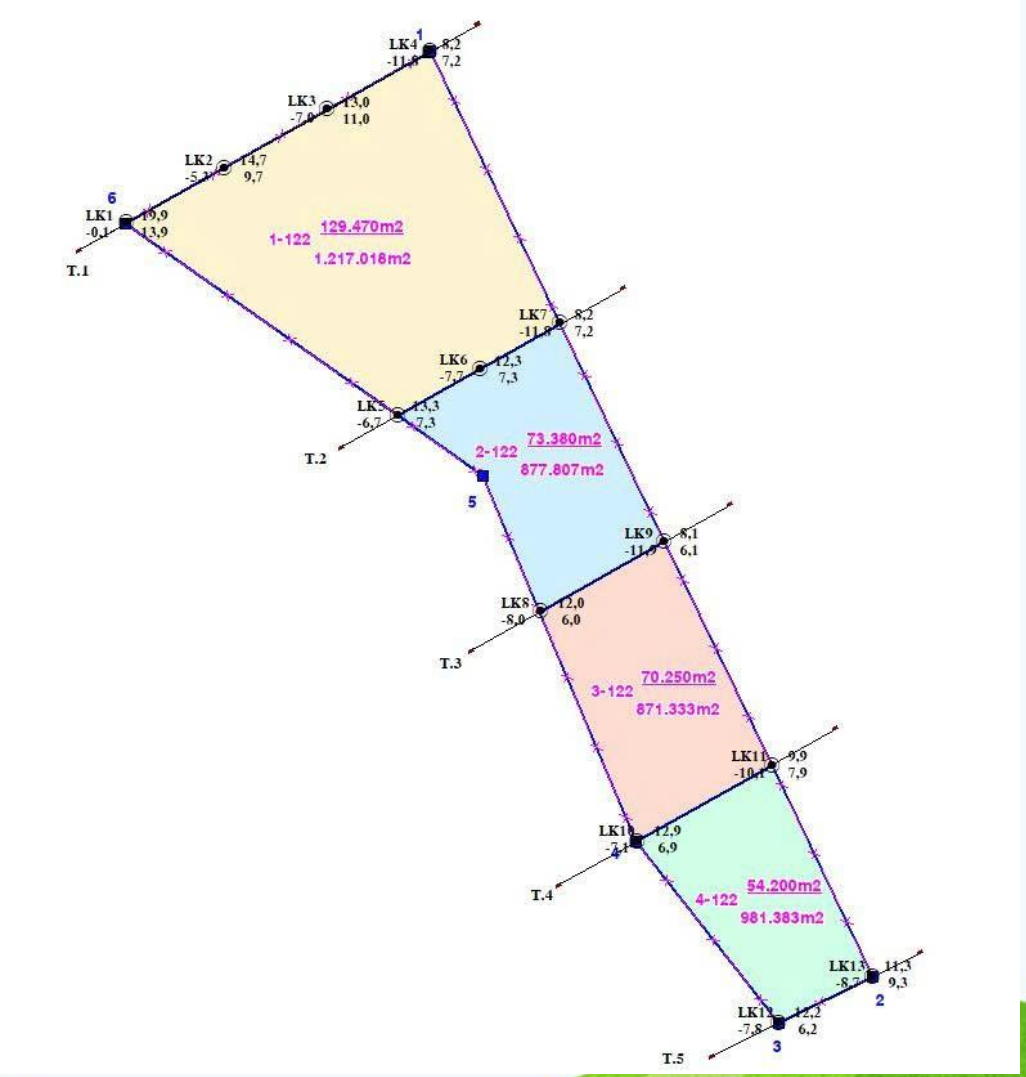

5 DỰ KIẾN PHƯƠNG PHÁP TÍNH TRỮ LƯỢNG

Bảng Tổng hợp các thông số tính trữ lượng

Khối - cấp trữ lượng	Số hiệu lỗ khoan	Cao độ LK (m)	Chiều sâu LK (m)	Bề dày dự kiến vật liệu (m)		Diện tích tính trữ lượng (m2)	Cote tính từ địa hình nguyên thủy (m)
				Lớp phủ (m)	Cát san lấp (m)		
1-122	LK1	-0,1	19,9	6,0	13,9	129.470	-20,0
	LK2	-5,3	14,7	5,0	9,7		
	LK3	-7,0	13,0	2,0	11,0		
	LK4	-11,8	8,2	1,0	7,2		
	LK5	-6,7	13,3	6,0	7,3		
	LK6	-7,7	12,3	5,0	7,3		
Trung bình		**-6,43**	**13,57**	**4,17**	**9,40**		
2-122	LK5	-6,7	13,3	6,0	7,3	73.380	
	LK6	-7,7	12,3	5,0	7,3		
	LK7	-11,8	8,2	1,0	7,2		
	LK8	-8,0	12,0	6,0	6,0		
	LK9	-11,9	8,1	2,0	6,1		
Trung bình		**-9,22**	**10,78**	**4,00**	**6,78**		
3-122	LK8	-8,0	12,0	6,0	6,0	70.250	
	LK9	-11,9	8,1	2,0	6,1		
	LK10	-7,1	12,9	6,0	6,9		
	LK11	-10,1	9,9	2,0	7,9		
Trung bình		**-9,28**	**10,73**	**4,00**	**6,73**		
4-122	LK10	-7,1	12,9	6,0	6,9	54.200	
	LK11	-10,1	9,9	2,0	7,9		
	LK12	-7,8	12,2	6,0	6,2		
	LK13	-8,7	11,3	2,0	9,3		
Trung bình		**-8,43**	**11,58**	**4,00**	**7,58**		

5 DỰ KIẾN PHƯƠNG PHÁP TÍNH TRỮ LƯỢNG

Bảng dự tính trữ lượng mỏ

Khối - cấp trữ lượng	Diện tích khối (m^2)	Bề dày dự kiến vật liệu (m)		Trữ lượng dự kiến vật liệu (m3)	
		Lớp phủ	Cát san lấp	Lớp phủ	Cát san lấp
1-122	129.470	4,17	9,40	539.890	1.217.018
2-122	73.380	4,00	6,78	293.520	497.516
3-122	70.250	4,00	6,73	281.000	472.783
4-122	54.200	4,00	7,58	216.800	410.836
Tổng	**327.300**			**1.331.210**	**2.598.153**
				3.929.363	

Như vậy:

+ Diện tích thân khoáng cát là: **32,73ha.**

+ Trữ lượng lớp phủ: **1.331.210 m^3.**

+ Trữ lượng khoáng sản cát lòng sông: **2.598.153 m^3**.

6 TỔ CHỨC THI CÔNG

Tổng thời gian thi công Đề án thăm dò, Lập báo cáo tổng kết trình Hội đồng thẩm định phê duyệt là 03 tháng, kể từ ngày phê duyệt Giấy phép thăm dò

STT	Hạng mục thực hiện	Thời gian thực hiện (tháng)		
		1	2	3
I	**Lập Đề án, xin giấy phép thăm dò**			
II	**Thi công Đề án**			
1	Công tác trắc địa			
2	Công tác đo vẽ lập bản đồ địa chất			
3	Công tác đo vẽ lập bản đồ ĐCTV-ĐCCT			
4	Công tác công trình thăm dò			
5	Công tác lấy mẫu, gia công, phân tích			
6	Công tác tổng kết, viết báo cáo			
7	Thẩm định, trình duyệt			
8	Can in xuất bản, nộp lưu trữ			

7 DỰ TOÁN KINH PHÍ

Cơ sở lập dự toán

- Quyết định số 1655/QĐ-BTNMT ngày 19/6/2024 của Bộ TN&MT về việc Ban hành Bộ đơn giá sản phẩm dịch vụ sự nghiệp công lĩnh vực địa chất khoáng sản sử dụng ngân sách nhà nước (theo mức lương cơ sở 1.800.000 đồng/tháng).
- Chi phí giám sát thăm dò thực hiện theo Nghị định số 21/2026/NĐ-CP ngày 16/01/2026 của Chính Phủ.
- Thông tư số 136/2017/TT-BTC ngày 22/12/2017 về việc Quy định lập, quản lý, sử dụng kinh phí của hoạt động kinh tế đối với các nhiệm vụ chi tiết về tài nguyên môi trường.
- Thông tư số 191/2016/TT-BTC ngày 08/11/2016 của Bộ Tài chính quy định mức thu, chế độ thu, nộp quản lý và sử dụng phí thẩm định đánh giá trữ lượng khoáng sản và lệ phí cấp phép hoạt động khoáng sản.

Tổng chi phí thăm dò

714.961.303 đồng

Giá thành thăm dò cát san lấp là

275 đ/m^3

8 KẾT LUẬN

Đề án thăm dò khoáng sản cát sông tại mỏ Phú Thứ - Tân Phú tại phường Hưng Phú, thành phố Cần Thơ được xây dựng trên cơ sở tài liệu đáng tin cậy và đề ra được các phương pháp và khối lượng thăm dò hợp lý.

Nội dung đề án được lập theo được lập theo mẫu số 01, phụ lục VI Thông tư số 40/2025/TT-BNNMT ngày 02/7/2025 của Bộ Nông nghiệp và Môi trường.

Đề án thăm dò với diện tích **32,73ha**, trữ lượng cát san lấp thăm dò dự tính đến cấp 122 đạt **2.598.153** m^3. Với trữ lượng trên có thể đáp ứng nhu cầu sử dụng vật liệu xây dựng thông thường phục vụ cho các công trình trọng điểm, vốn ngân sách nhà nước hiện nay trên địa bàn tỉnh.

- Tổng dự toán thăm dò là **714.961.303 đồng**. Giá thành thăm dò cát san lấp là **275 đ/m^3** là phù hợp với giá thăm dò trên thị trường và phù hợp với khả năng tài chính của Công ty.

Để triển khai công tác thăm dò, đánh giá trữ lượng làm cơ sở xin cấp giấy phép khai thác mỏ theo quy định của Luật Địa chất và Khoáng sản và Nghị quyết số 66.4/2025/NQ-CP ngày 21 tháng 9 năm 2025 của Chính phủ về các cơ chế, chính sách đặc thù nhằm tháo gỡ khó khăn trong triển khai Luật Địa chất và khoáng sản năm 2024. Công ty Cổ phần khoáng sản Thuận Phong kính đề nghị Ủy ban nhân dân thành phố Cần Thơ, Sở Nông nghiệp và Môi trường tổ chức thẩm định, phê duyệt Đề án và cấp giấy phép thăm dò để Công ty sớm triển khai thực hiện công tác thăm dò theo quy định hiện hành.