SƠ ĐỒ ĐỊA CHẤT, BỐ TRÍ CÔNG TRÌNH VÀ LẤY MẪU

ĐÁ LÀM VẬT LIỆU XÂY DỰNG THÔNG THƯỜNG TẠI MỎ ĐÁ HÀ SƠN
THUỘC XÃ ĐỒNG THỌ, XÃ BÌNH CA, XÃ SƠN DƯƠNG, TỈNH TUYÊN QUANG

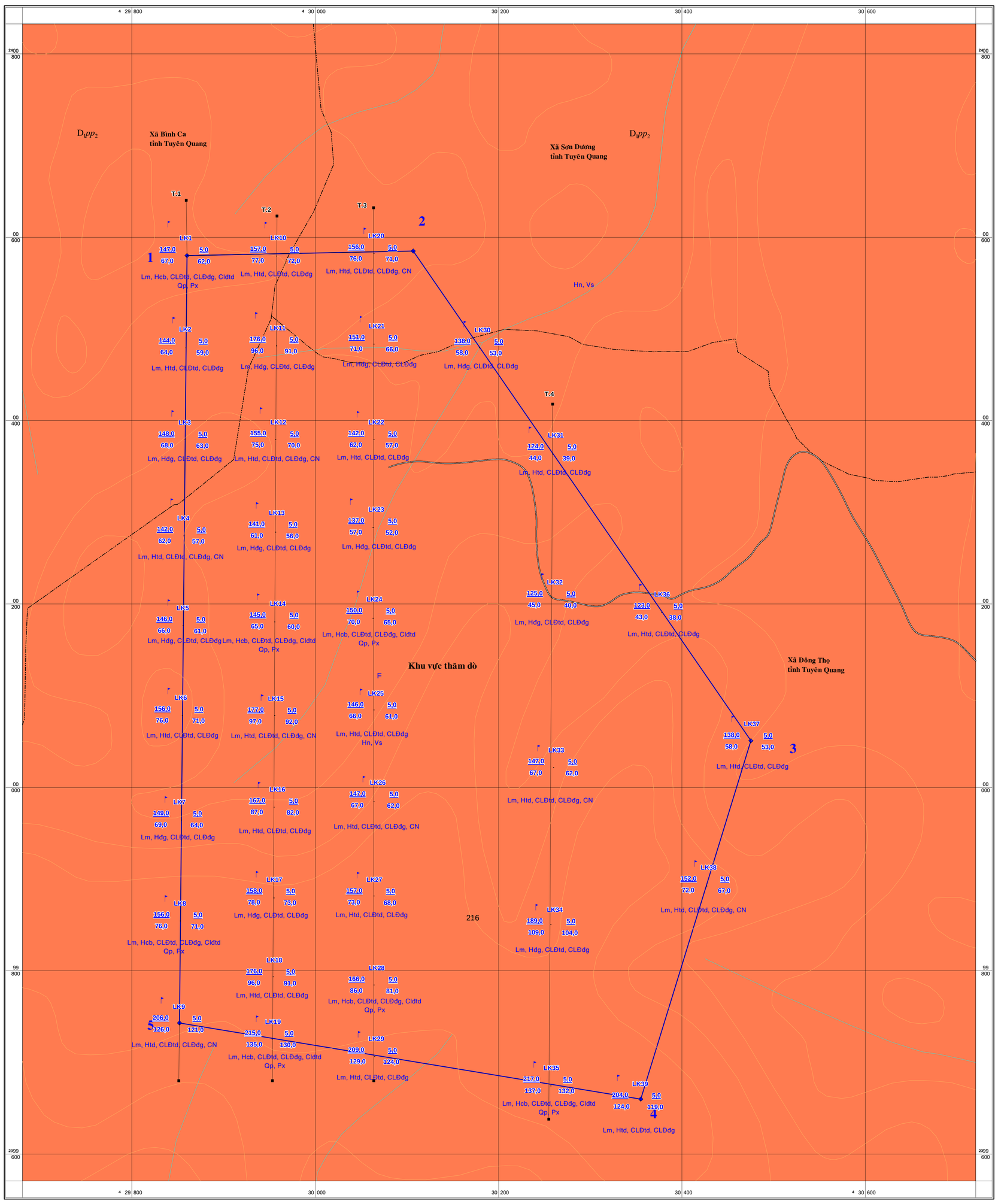

TỶ LỆ 1:2.000

1cm trên bản đồ bằng 20m ngoài thực tế

CHỈ DẪN

I. ĐỊA CHẤT

Hệ tầng Pia Phương
Phân hệ tầng trên: Đá phiến sericit, cát kết dạng quarzit. Dày 1200m

Ranh giới địa chất.

Ranh giới lớp đất đá

II. THẠCH HỌC

Sét bột

Cát kết

III. CÔNG TRÌNH

Lỗ khoan thăm dò

1- Số hiệu lỗ khoan.
2- Cao độ miệng lỗ khoan (m).
3- Chiều sâu lỗ khoan (m).
4- Bề dày lớp đất phủ (m).
5- Bề dày lớp đá cứng đến cote +80m (m).

Tuyến công trình thăm dò

Vị trí quan trắc mực nước trong lỗ khoan.

Vị trí bơm nước thí nghiệm.

Lm - Mẫu thạch học lát mỏng
Qp - Mẫu quang phổ
CLĐtd - Mẫu cơ lý đá toàn diện
CLĐđg - Mẫu cơ lý đáđơn giản
Htd - Mẫu hóa toàn diện
Hđg - Mẫu hóa đơn giản
Px - Mẫu phóng xạ
CN - Mẫu công nghệ
Hn - Mẫu hóa nước
Vs- Mẫu vi sinh

Ký hiệu lỗ khoan trên mặt cắt

1 - Số hiệu lỗ khoan;
2 - Cao độ miệng lỗ khoan (m);
3 - Chiều sâu lỗ khoan (m);
4 - Bề dày lớp phủ (m);
5 - Bề dày lớp đá cứng đến cote +80m (m).

IV. KÝ HIỆU KHÁC

Ranh giới khu vực thăm dò và điểm góc

216 Độ cao điểm chi tiết địa hình

Đường đồng mức

Đường giao thông

Suối

Ranh hành chính

Hệ tọa độ Vn2000, Kinh tuyến trục 106 độ múi chiếu 3 độ

CÔNG TY CỔ PHẦN KHOÁNG SẢN THUẬN PHONG		
ĐỀ ÁN THĂM DÒ KHOÁNG SẢN ĐÁ LÀM VẬT LIỆU XÂY DỰNG THÔNG THƯỜNG TẠI MỎ ĐÁ HÀ SƠN THUỘC XÃ ĐỒNG THỌ, XÃ BÌNH CA, XÃ SƠN DƯƠNG, TỈNH TUYÊN QUANG		
Bản vẽ số: 03	Tỷ lệ 1:2.000	Năm 2026
TÊN BẢN VẼ: SƠ ĐỒ ĐỊA CHẤT, BỐ TRÍ CÔNG TRÌNH VÀ LẤY MẪU		
Chức danh	Họ và tên	Ký tên
Người thành lập	Trần Thị Hoài Thương	
Người kiểm tra	Đinh Thị Mỹ Trinh	
Chủ biên		
CHỦ ĐẦU TƯ	ĐƠN VỊ TƯ VẤN	

MẶT CẮT ĐỊA CHẤT THEO TUYẾN
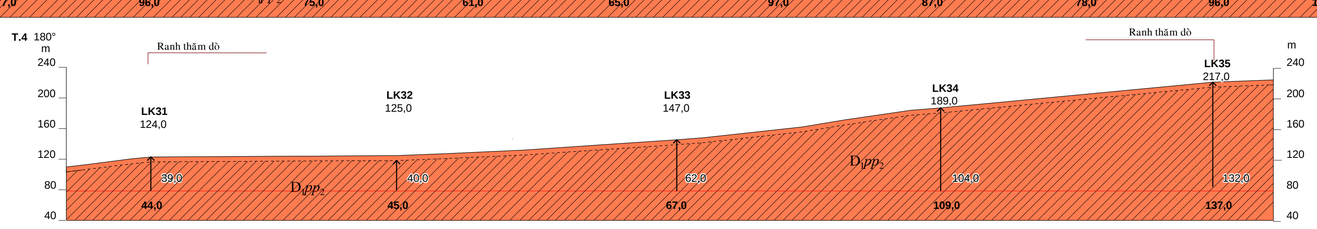
TỶ LỆ NGANG 1:2.000
TỶ LỆ ĐỨNG 1:4.000