BÌNH ĐỒ VÀ MẶT CẮT DỰ KIẾN TÍNH TRỮ LƯỢNG

ĐÁ LÀM VẬT LIỆU XÂY DỰNG THÔNG THƯỜNG TẠI MỎ ĐÁ HÀ SƠN

THUỘC XÃ ĐỒNG THỌ, XÃ BÌNH CA, XÃ SƠN DƯƠNG, TỈNH TUYÊN QUANG

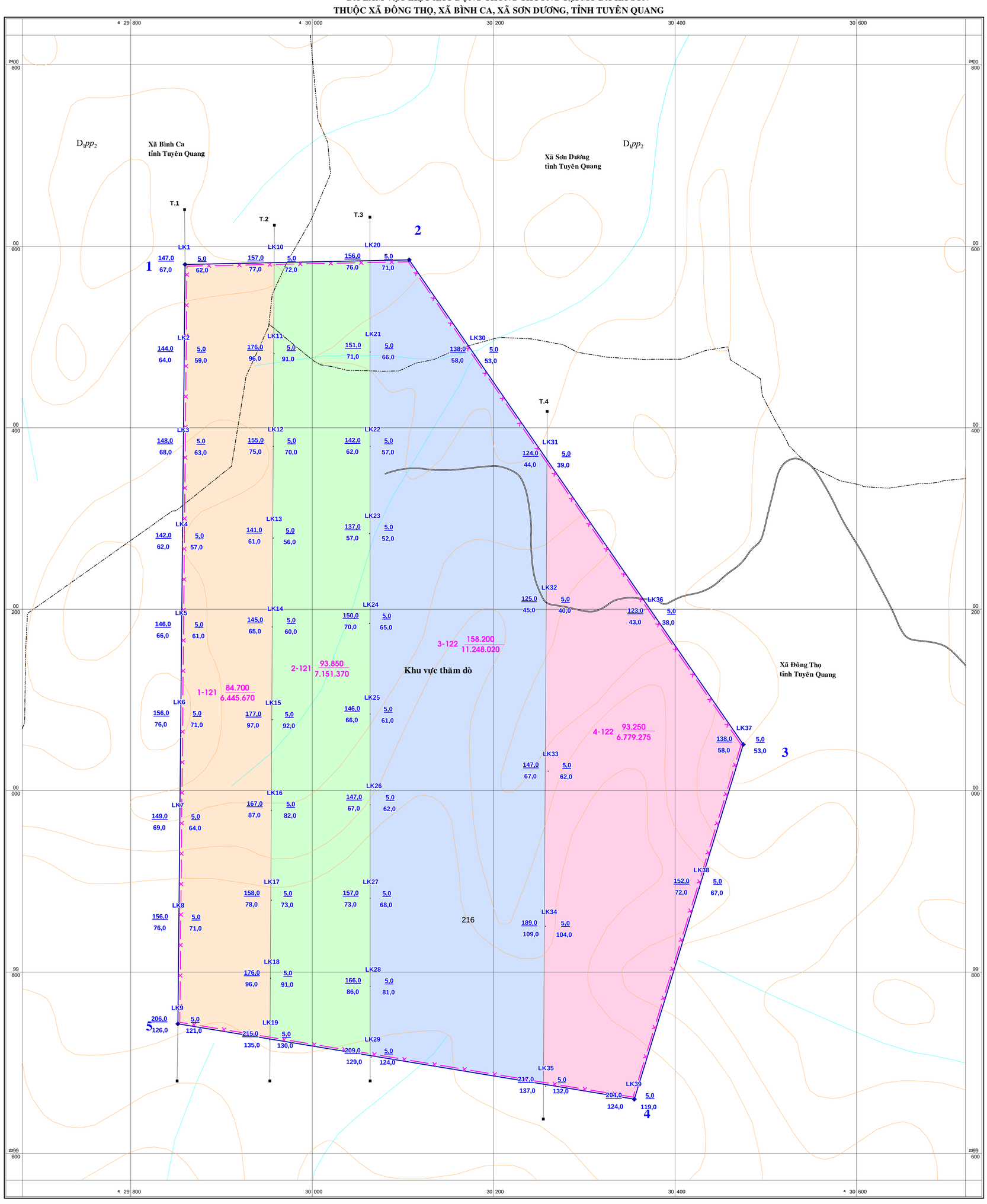

TỶ LỆ 1:2.000

1cm trên bản đồ bằng 20m ngoài thực tế

CHỈ DẪN

I. TRỮ LƯỢNG

Ranh giới tính trữ lượng

1-121 | 84.700 / 6.445.670 | Khối cấp trữ lượng | Diện tích khối trữ lượng (m2) / Trữ lượng đá xây dựng (m3)

II. ĐỊA CHẤT

D_1pp_2 — **Hệ tầng Pia Phương**
Phần hệ tầng trên: Đá phiến sericit, cát kết dạng quarzit. Dày 1200m

Ranh giới địa chất.

Ranh giới lớp đất đá

III. THẠCH HỌC

Sét bột

Cát kết

IV. CÔNG TRÌNH

Lỗ khoan thăm dò

1- Số hiệu lỗ khoan.
2- Cao độ miệng lỗ khoan (m).
3- Chiều sâu lỗ khoan (m).
4- Bề dày lớp đất phủ (m).
5- Bề dày lớp đá cứng đến cote +80m (m).

T.I — Tuyến công trình thăm dò

Ký hiệu lỗ khoan trên mặt cắt

1 - Số hiệu lỗ khoan;
2 - Cao độ miệng lỗ khoan (m);
3 - Chiều sâu lỗ khoan (m);
4 - Bề dày lớp phủ (m);
5 - Bề dày lớp đá cứng đến cote +80m (m).

V. KÝ HIỆU KHÁC

Ranh giới khu vực thăm dò và điểm góc

216 — Độ cao điểm chi tiết địa hình

Đường đồng mức

Đường giao thông

Suối

Ranh hành chính

Hệ tọa độ Vn2000, Kinh tuyến trục 106 độ múi chiếu 3 độ

Hệ tọa độ Vn2000, Kinh tuyến trục 106 độ múi chiếu 3 độ

CÔNG TY CỔ PHẦN KHOÁNG SẢN THUẬN PHONG		
ĐỀ ÁN THĂM DÒ KHOÁNG SẢN ĐÁ LÀM VẬT LIỆU XÂY DỰNG THÔNG THƯỜNG TẠI MỎ ĐÁ HÀ SƠN THUỘC XÃ ĐỒNG THỌ, XÃ BÌNH CA, XÃ SƠN DƯƠNG, TỈNH TUYÊN QUANG		
Bản vẽ số: 04	Tỷ lệ 1:2.000	Năm 2026
TÊN BẢN VẼ: BÌNH ĐỒ VÀ MẶT CẮT DỰ KIẾN TÍNH TRỮ LƯỢNG		
Chức danh	Họ và tên	Ký tên
Người thành lập	Trần Thị Hoài Thương	
Người kiểm tra	Đinh Thị Mỹ Trinh	
Chủ biên		
CHỦ ĐẦU TƯ	ĐƠN VỊ TƯ VẤN	

MẶT CẮT DỰ KIẾN TÍNH TRỮ LƯỢNG THEO TUYẾN
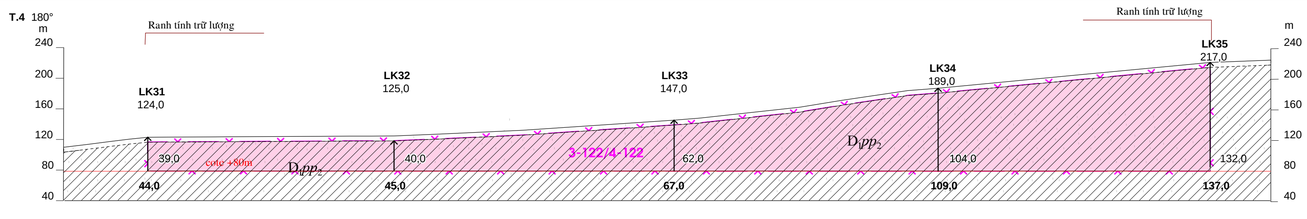
TỶ LỆ NGANG 1:2.000
TỶ LỆ ĐỨNG 1:4.000